Ссылка: https://datalens.yandex/agwiuokf29iut?_share_link=public

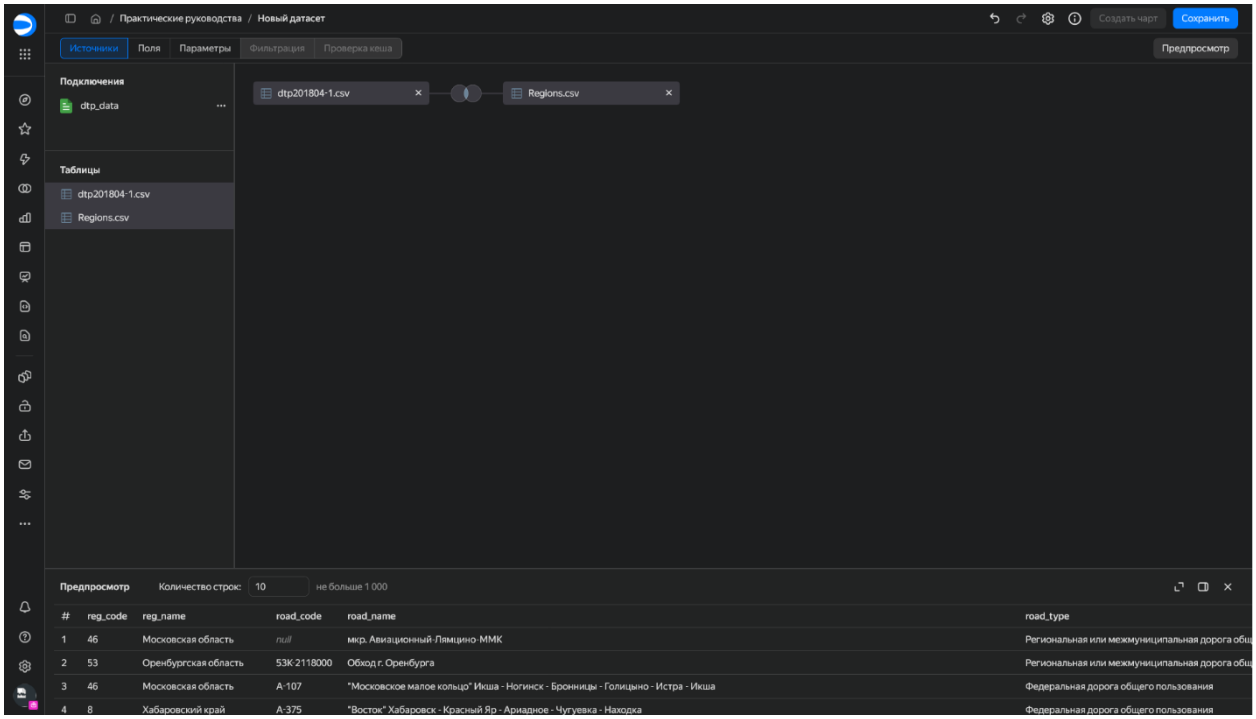

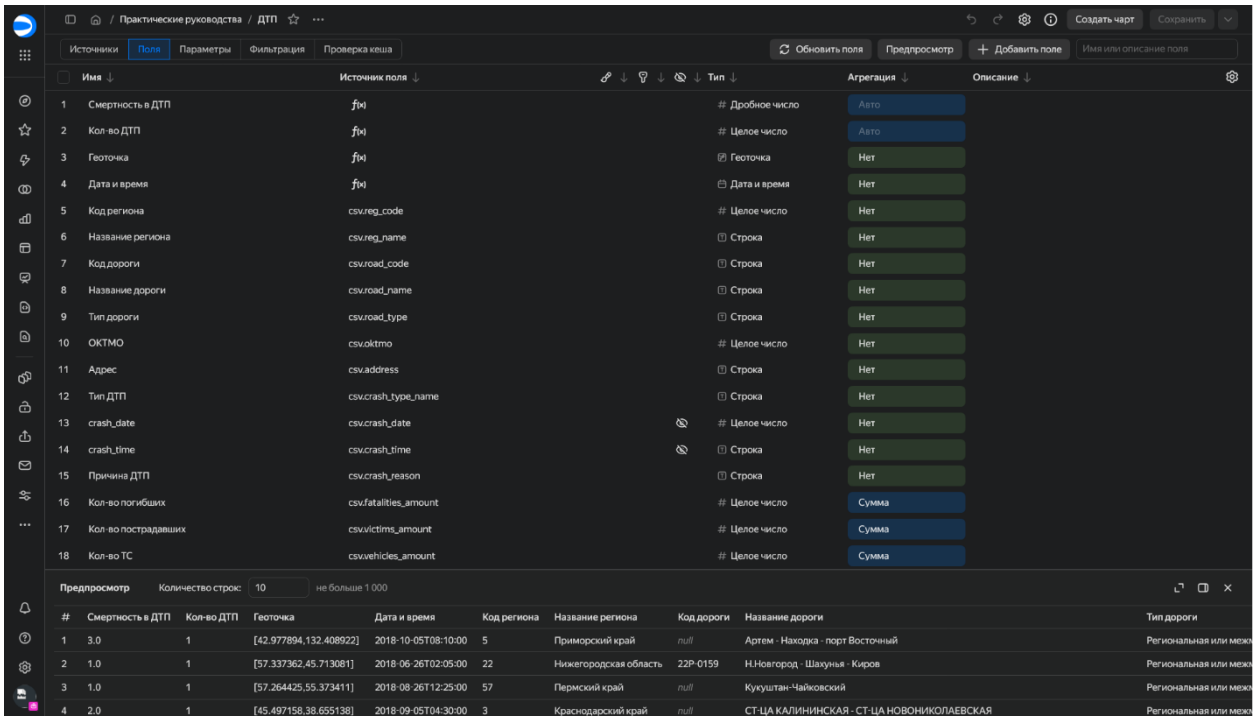

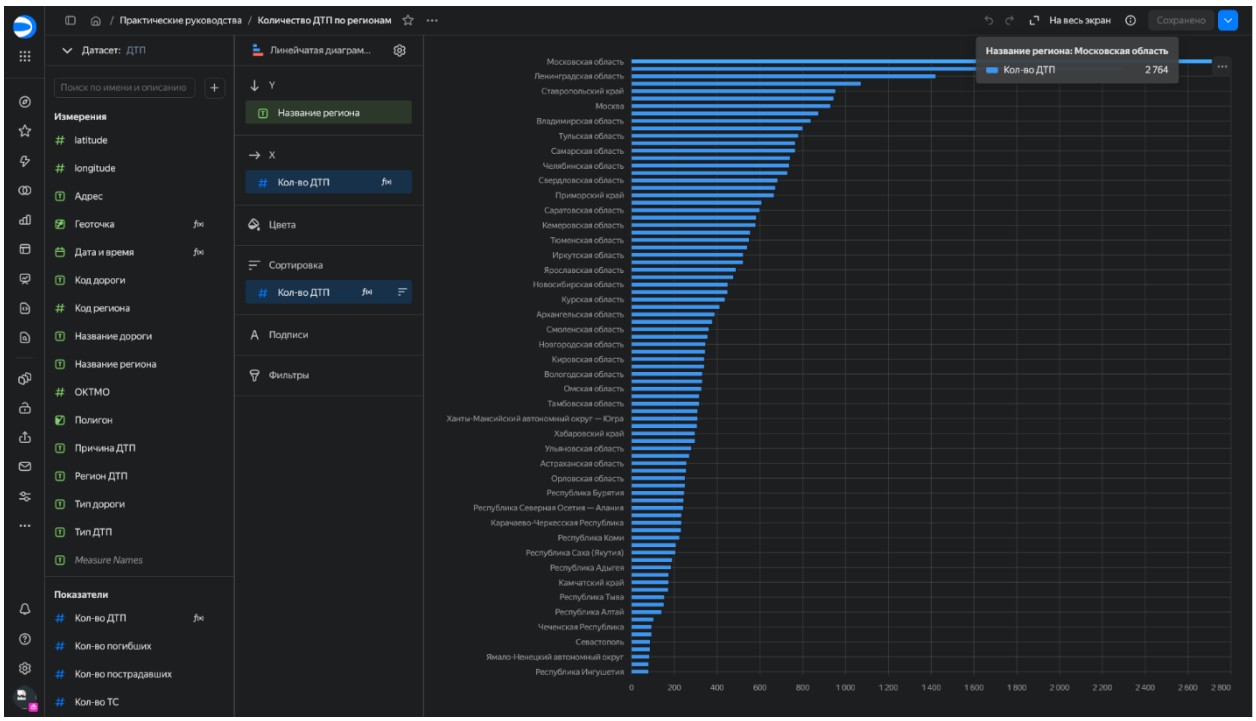
Практические руководства / Количество ДТП по регионам
На весь экран
Сохранено
Датасет: ДТП
Линейчатая диаграм...
Поиск по имени и описанию
Измерения
latitude
longitude
Адрес
Геточка
Дата и время
Код дороги
Код региона
Название дороги
Название региона
ОКТМО
Полигон
Причина ДТП
Регион ДТП
Тип дороги
Тип ДТП
Measure Names
Показатели
Кол-во ДТП
Кол-во погибших
Кол-во пострадавших
Кол-во ТС
Y
Название региона
X
Кол-во ДТП
Цвета
Сортировка
Кол-во ДТП
Подписи
Фильтры
Название региона: Московская область
Кол-во ДТП 2 764
Московская область
Ленинградская область
Ставропольский край
Москва
Владимирская область
Тульская область
Самарская область
Челябинская область
Свердловская область
Приморский край
Саратовская область
Кемеровская область
Тюменская область
Иркутская область
Ярославская область
Новосибирская область
Курская область
Архангельская область
Смоленская область
Новгородская область
Кировская область
Вологодская область
Омская область
Тамбовская область
Ханты-Мансийский автономный округ — Югра
Хабаровский край
Ульяновская область
Астраханская область
Орловская область
Республика Бурятия
Республика Северная Осетия — Алания
Карачаево-Черкесская Республика
Республика Коми
Республика Саха (Якутия)
Республика Адыгея
Камчатский край
Республика Тыва
Республика Алтай
Чеченская Республика
Севастополь
Ямало-Ненецкий автономный округ
Республика Ингушетия
0 200 400 600 800 1 000 1 200 1 400 1 600 1 800 2 000 2 200 2 400 2 600 2 800

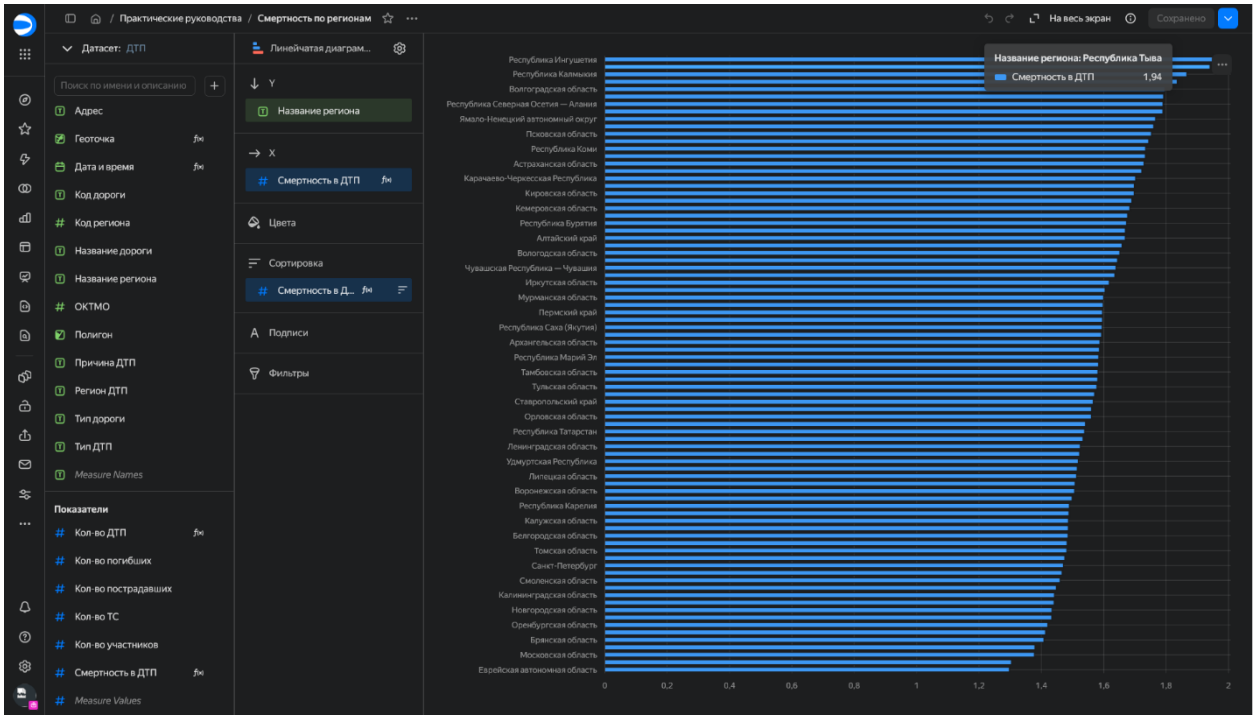
Практические руководства / Смертность по регионам
На весь экран
Сохранено
Датасет: ДТП
Линейчатая диаграм...
Поиск по имени и описанию
Адрес
Геточка
Дата и время
Код дороги
Код региона
Название дороги
Название региона
ОКТМО
Полигон
Причина ДТП
Регион ДТП
Тип дороги
Тип ДТП
Measure Names
Показатели
Кол-во ДТП
Кол-во погибших
Кол-во пострадавших
Кол-во ТС
Кол-во участников
Смертность в ДТП
Measure Values
Y
Название региона
X
Смертность в ДТП
Цвета
Сортировка
Смертность в Д...
Подписи
Фильтры
Название региона: Республика Тыва
Смертность в ДТП 1,94
Республика Ингушетия
Республика Калмыкия
Волгоградская область
Республика Северная Осетия — Алания
Ямало-Ненецкий автономный округ
Псковская область
Республика Коми
Астраханская область
Карачаево-Черкесская Республика
Кировская область
Кемеровская область
Республика Бурятия
Алтайский край
Вологодская область
Чувашская Республика — Чувашия
Иркутская область
Мурманская область
Пермский край
Республика Саха (Якутия)
Архангельская область
Республика Марий Эл
Тамбовская область
Тульская область
Ставропольский край
Орловская область
Республика Татарстан
Ленинградская область
Удмуртская Республика
Липецкая область
Воронежская область
Республика Карелия
Калужская область
Белгородская область
Томская область
Санкт-Петербург
Смоленская область
Калининградская область
Новгородская область
Оренбургская область
Брянская область
Московская область
Еврейская автономная область
0 0,2 0,4 0,6 0,8 1 1,2 1,4 1,6 1,8 2

Практические руководства / Кол-во ДТП и смертность по неделям
На весь экран
Сохранено
Датасет: ДТП
Линейная диаграмма
Поиск по имени и описанию
Адрес
Геоточка
Дата и время
Код дороги
Код региона
Название дороги
Название региона
ОКТМО
Полигон
Причина ДТП
Регион ДТП
Тип дороги
Тип ДТП
Measure Names
Показатели
Кол-во ДТП
Кол-во погибших
Кол-во пострадавших
Кол-во ТС
Кол-во участников
Смертность в ДТП
Measure Values
X
Дата и время
Y
Кол-во ДТП
Y2
Смертность в ДТП
Цвета
Measure Names
Формы
Measure Names
Сортировка
Подписи
Сплит beta
Фильтры
31 декабря 2018
Кол-во ДТП 137
Смертность в ДТП 1,73
Сумма 138,73
Апр. '18
Май '18
Июнь '18
Июль '18
Авг. '18
Сент. '18
Окт. '18
Нояб. '18
Дек. '18
Янв. '19
Кол-во ДТП
Смертность в ДТП

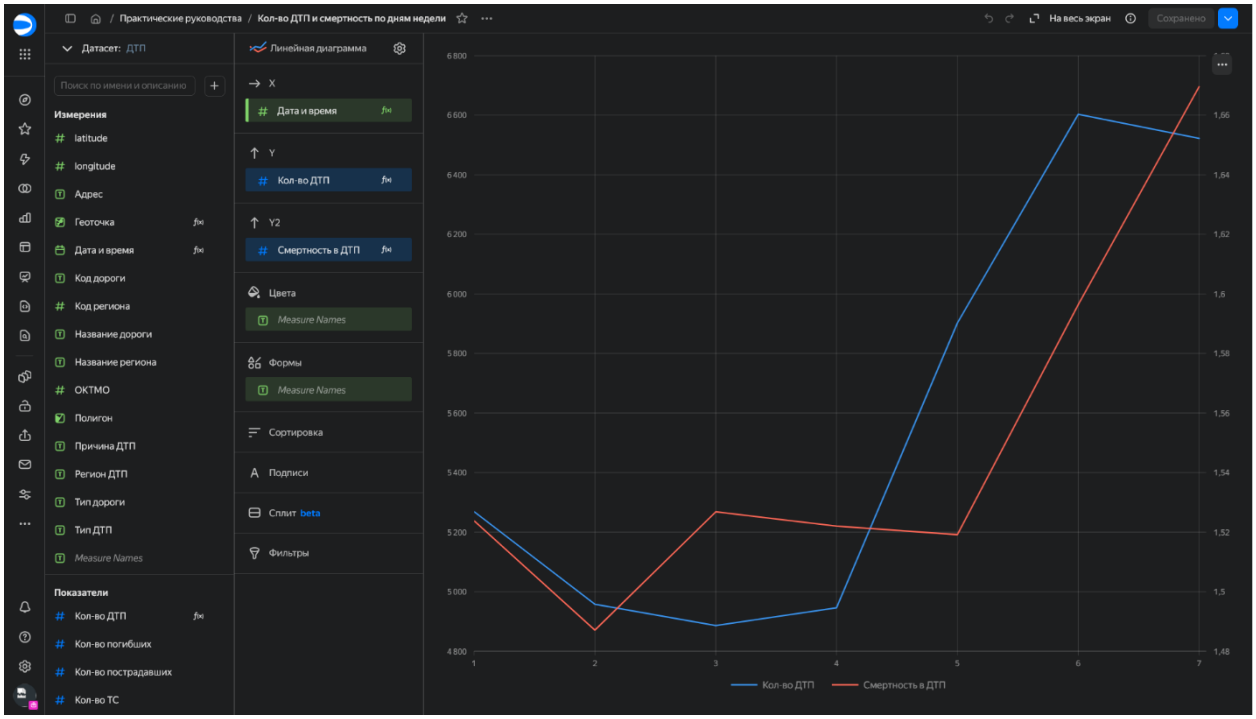
Практические руководства / Кол-во ДТП и смертность по дням недели
На весь экран
Сохранено
Датасет: ДТП
Линейная диаграмма
Поиск по имени и описанию
Измерения
latitude
longitude
Адрес
Геоточка
Дата и время
Код дороги
Код региона
Название дороги
Название региона
ОКТМО
Полигон
Причина ДТП
Регион ДТП
Тип дороги
Тип ДТП
Measure Names
Показатели
Кол-во ДТП
Кол-во погибших
Кол-во пострадавших
Кол-во ТС
X
Дата и время
Y
Кол-во ДТП
Y2
Смертность в ДТП
Цвета
Measure Names
Формы
Measure Names
Сортировка
Подписи
Сплит beta
Фильтры
Кол-во ДТП
Смертность в ДТП

Практические руководства / Кол-во ДТП и смертность по часам в течение дня
На весь экран
Сохранено
Датасет: ДТП
Линейная диаграмма
Измерения
latitude
longitude
Адрес
Геточка
Дата и время
Код дороги
Код региона
Название дороги
Название региона
ОКТМО
Полигон
Причина ДТП
Регион ДТП
Тип дороги
Тип ДТП
Measure Names
Показатели
Кол-во ДТП
Кол-во погибших
Кол-во пострадавших
Кол-во ТС
X
Дата и время
Y
Кол-во ДТП
Y2
Смертность в ДТП
Цвета
Measure Names
Формы
Measure Names
Сортировка
Подписи
Сплит beta
Фильтры
Кол-во ДТП
Смертность в ДТП

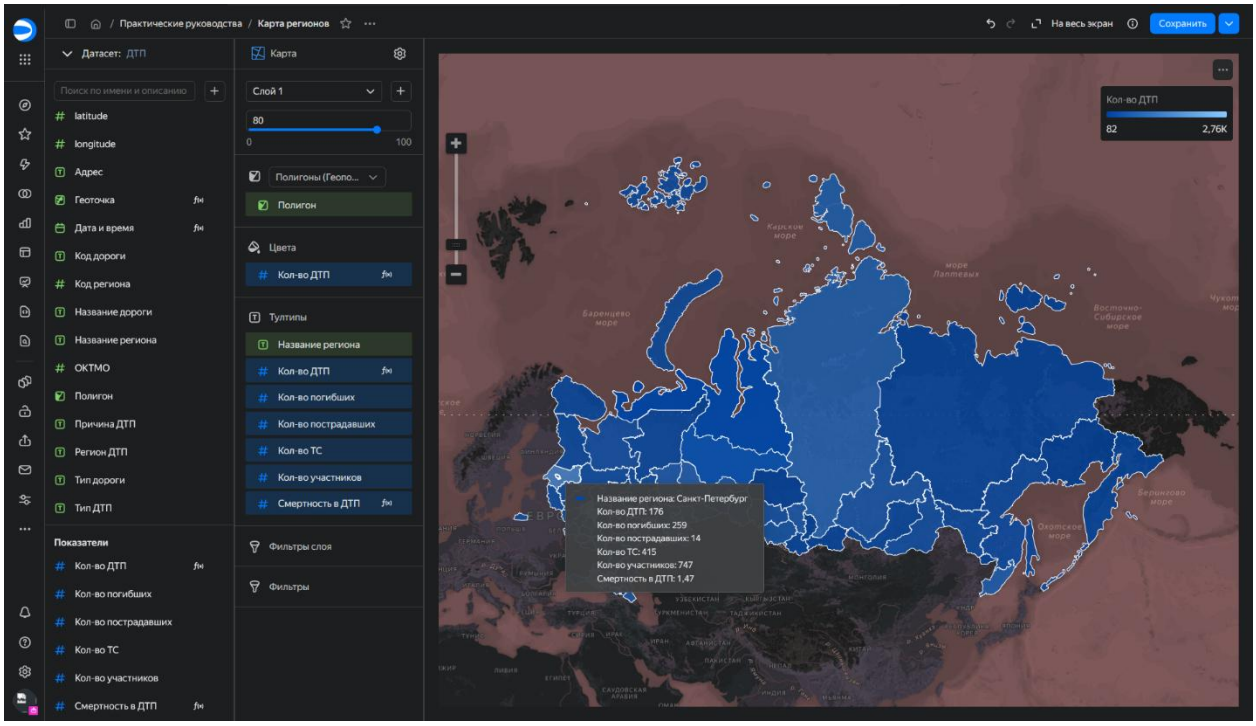
Практические руководства / Карта регионов
На весь экран
Сохранить
Датасет: ДТП
Карта
Слой 1
Полигоны (Геопо...
Полигон
Цвета
Кол-во ДТП
Тултипы
Название региона
Кол-во ДТП
Кол-во погибших
Кол-во пострадавших
Кол-во ТС
Кол-во участников
Смертность в ДТП
Фильтры слоя
Фильтры
Кол-во ДТП
82
2,76K
Название региона: Санкт-Петербург
Кол-во ДТП: 176
Кол-во погибших: 259
Кол-во пострадавших: 14
Кол-во ТС: 415
Кол-во участников: 747
Смертность в ДТП: 1,47

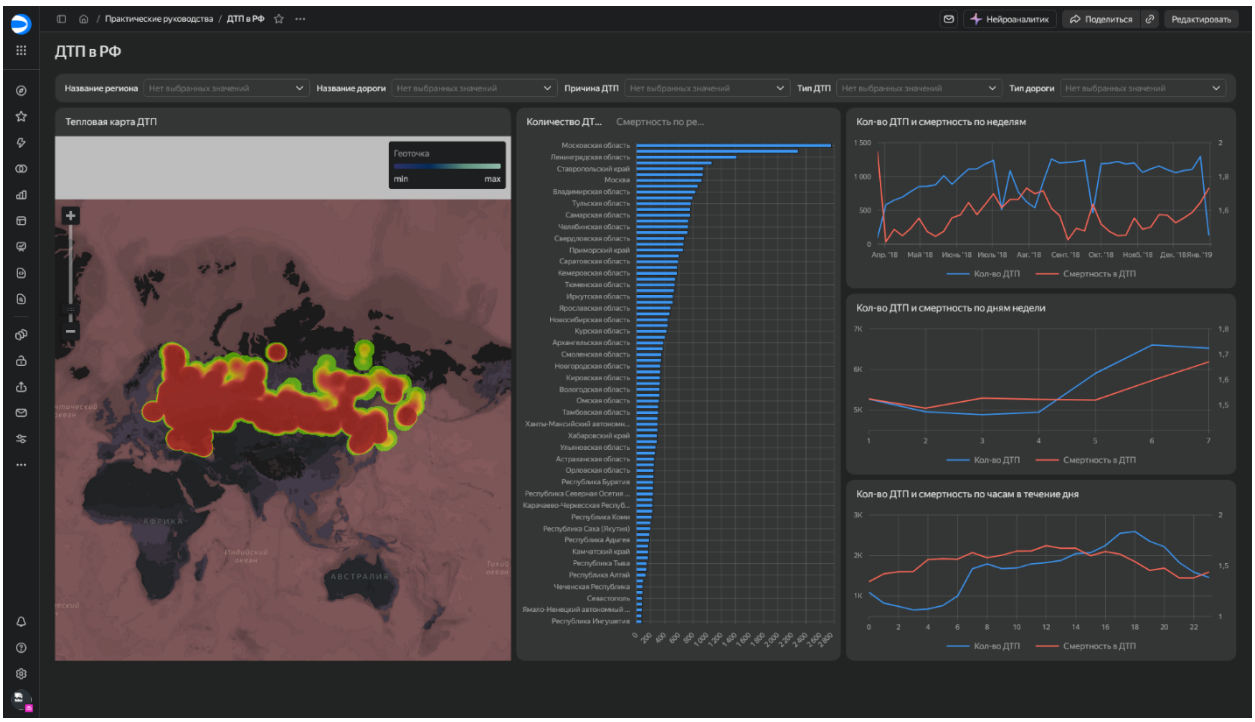
Практические руководства / ДТП в РФ
Нейроаналитик
Поделиться
Редактировать
ДТП в РФ
Название региона
Название дороги
Причина ДТП
Тип ДТП
Тип дороги
Тепловая карта ДТП
Геточка
min
max
Количество ДТ...
Смертность по ре...
Кол-во ДТП и смертность по неделям
Кол-во ДТП и смертность по дням недели
Кол-во ДТП и смертность по часам в течение дня
Кол-во ДТП
Смертность в ДТП

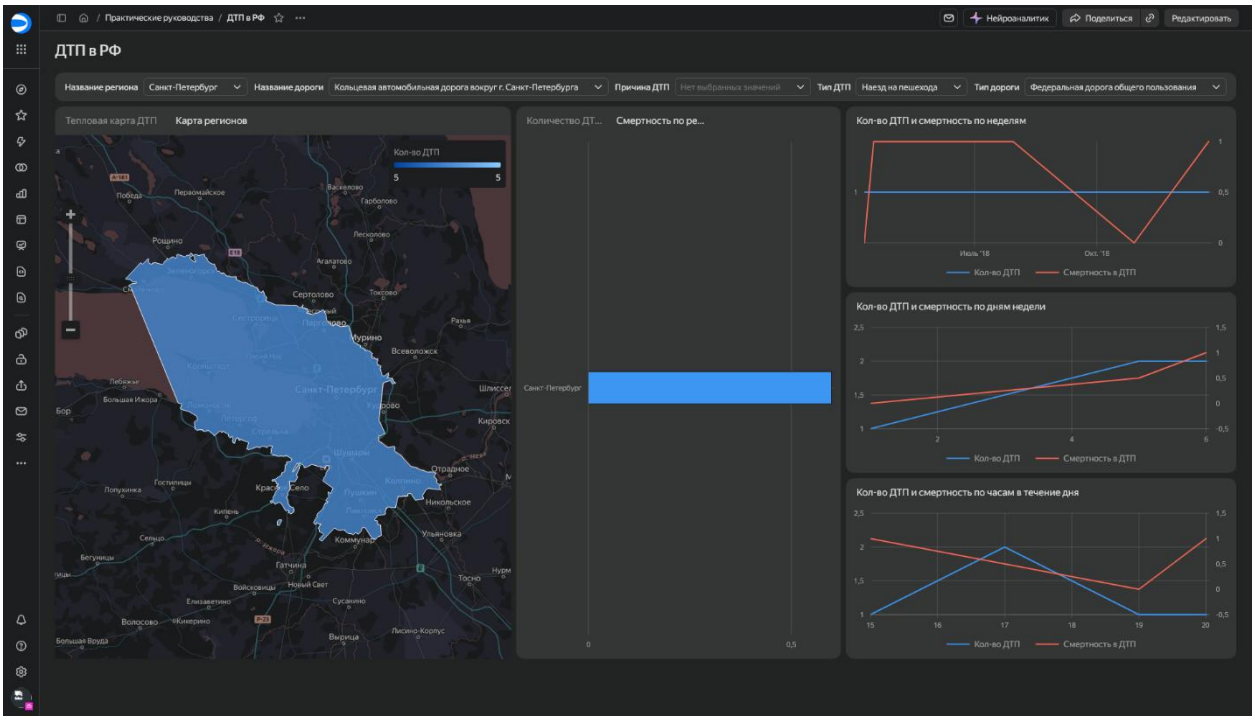
Практические руководства / ДТП в РФ
Нейроаналитик
Поделиться
Редактировать
ДТП в РФ
Название региона
Санкт-Петербург
Название дороги
Кольцевая автомобильная дорога вокруг г. Санкт-Петербурга
Причина ДТП
Тип ДТП
Наезд на пешехода
Тип дороги
Федеральная дорога общего пользования
Тепловая карта ДТП
Карта регионов
Кол-во ДТП
Количество ДТ...
Смертность по ре...
Кол-во ДТП и смертность по неделям
Кол-во ДТП и смертность по дням недели
Кол-во ДТП и смертность по часам в течение дня
Кол-во ДТП
Смертность в ДТП

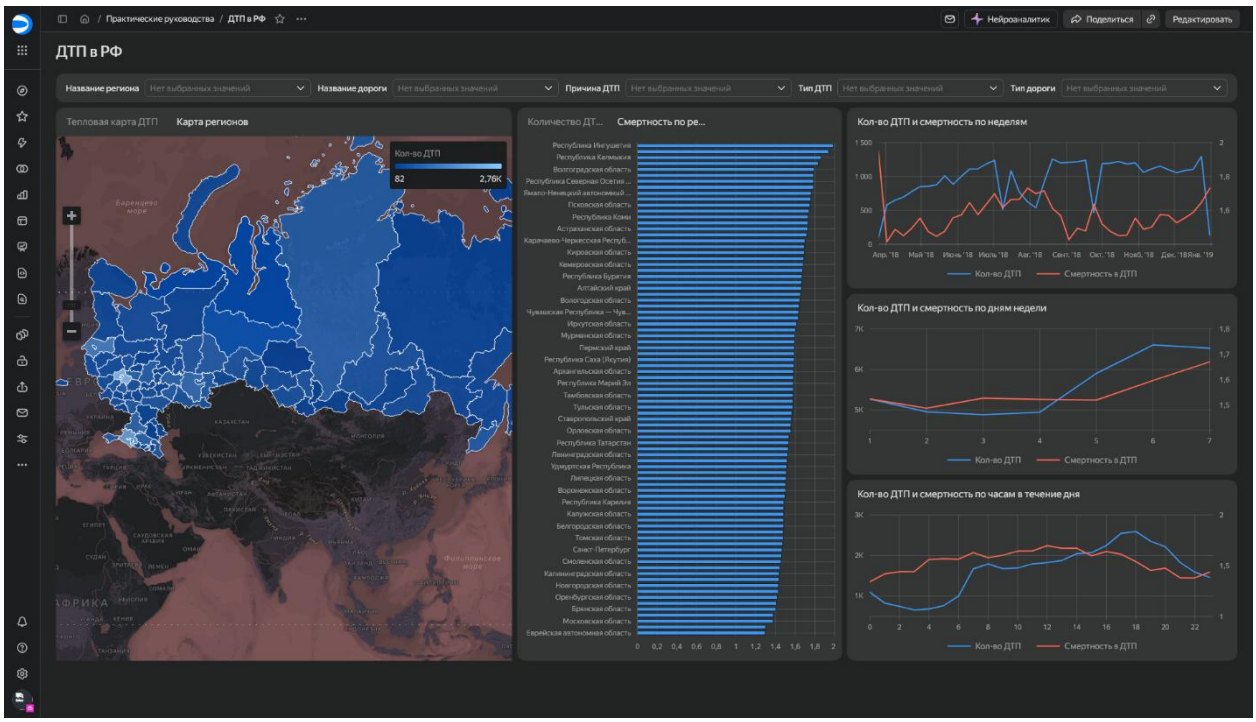
Практические руководства / ДТП в РФ
Нейроаналитик
Поделиться
Редактировать
ДТП в РФ
Название региона
Нет выбранных значений
Название дороги
Нет выбранных значений
Причина ДТП
Нет выбранных значений
Тип ДТП
Нет выбранных значений
Тип дороги
Нет выбранных значений
Тепловая карта ДТП
Карта регионов
Кол-во ДТП
82
2,76K
Количество ДТ...
Смертность по ре...
Кол-во ДТП и смертность по неделям
Кол-во ДТП
Смертность в ДТП
Кол-во ДТП и смертность по дням недели
Кол-во ДТП
Смертность в ДТП
Кол-во ДТП и смертность по часам в течение дня
Кол-во ДТП
Смертность в ДТП